Actividad Semana 2 Curso 4

1. se disena la vista con 4 lugares definidos =

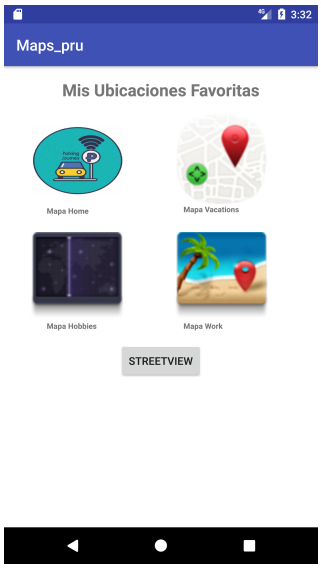

Al Hacer Clic sobre cada uno seguimos a la ubicación del mismo en el mapa con un icono personalizado como lo indica la actividad=

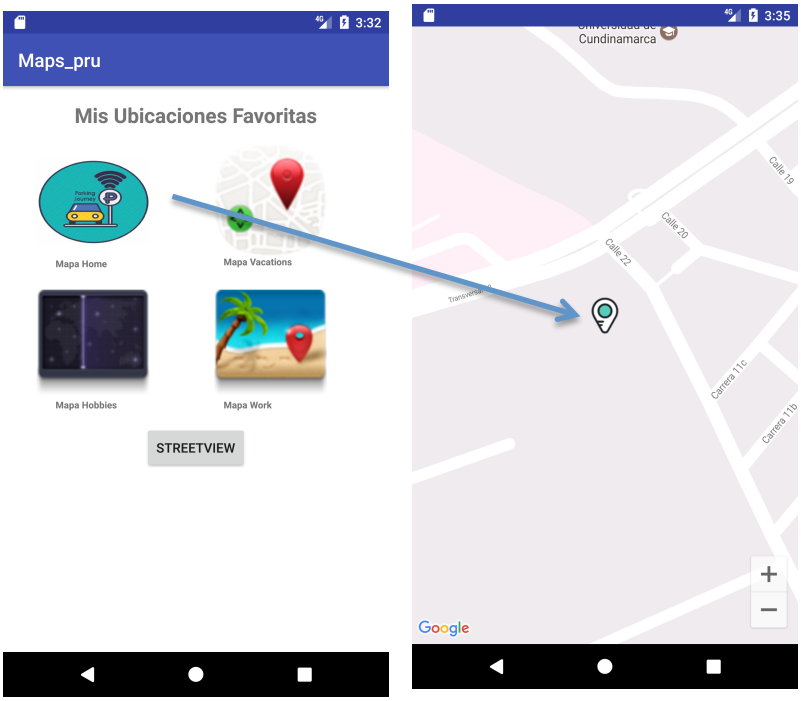

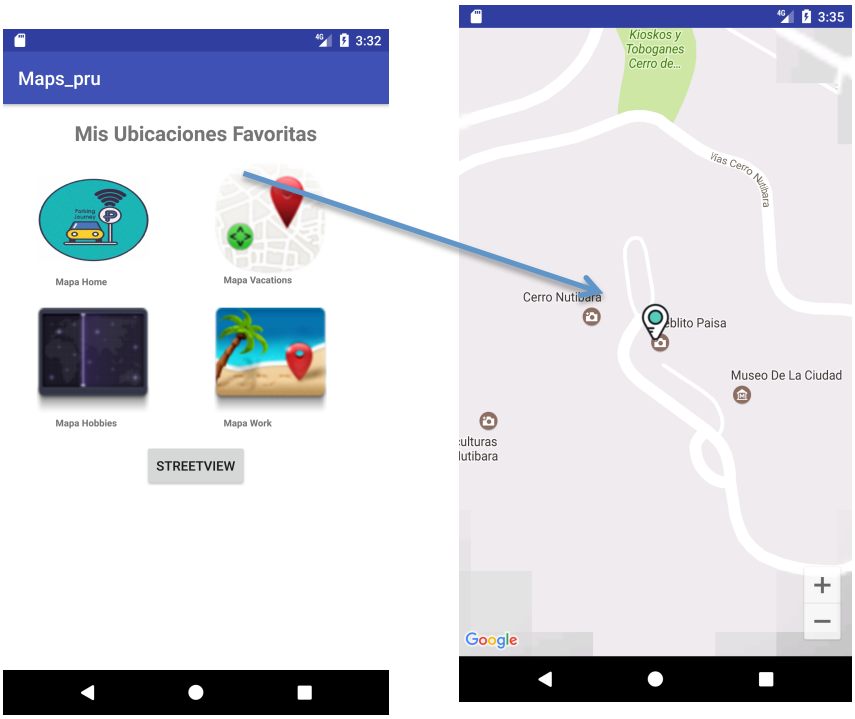
3:32
Maps_pru
Mis Ubicaciones Favoritas
Mapa Home
Mapa Vacations
Mapa Hobbies
Mapa Work
STREETVIEW
3:35
Kioskos y Toboganes Cerro de...
Vías Cerro Nutibara
Cerro Nutibara
Museo De La Ciudad
Google

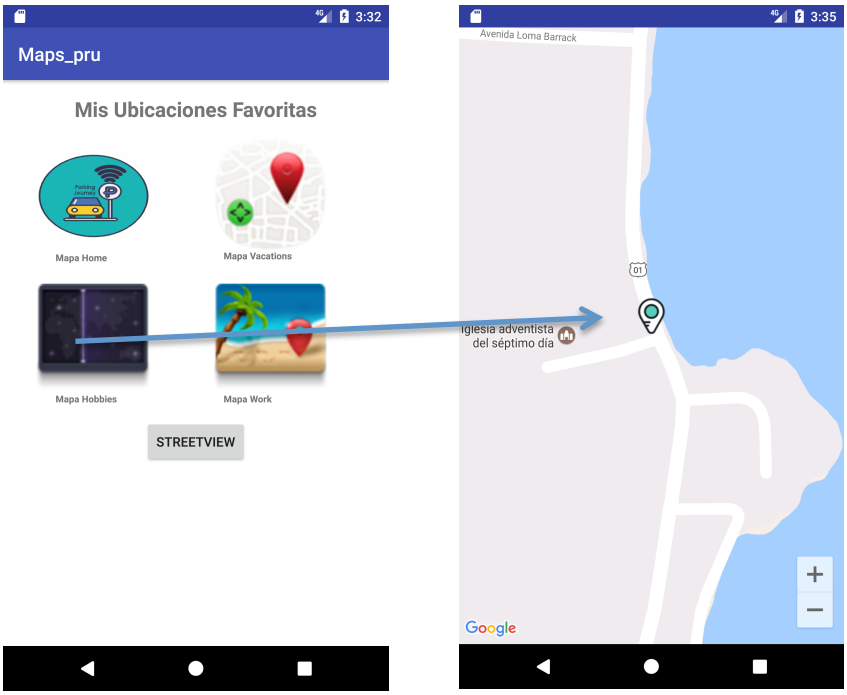
3:32
Maps_pru
Mis Ubicaciones Favoritas
Mapa Home
Mapa Vacations
Mapa Hobbies
Mapa Work
STREETVIEW
3:35
Avenida Loma Barrack
del séptimo día
Google

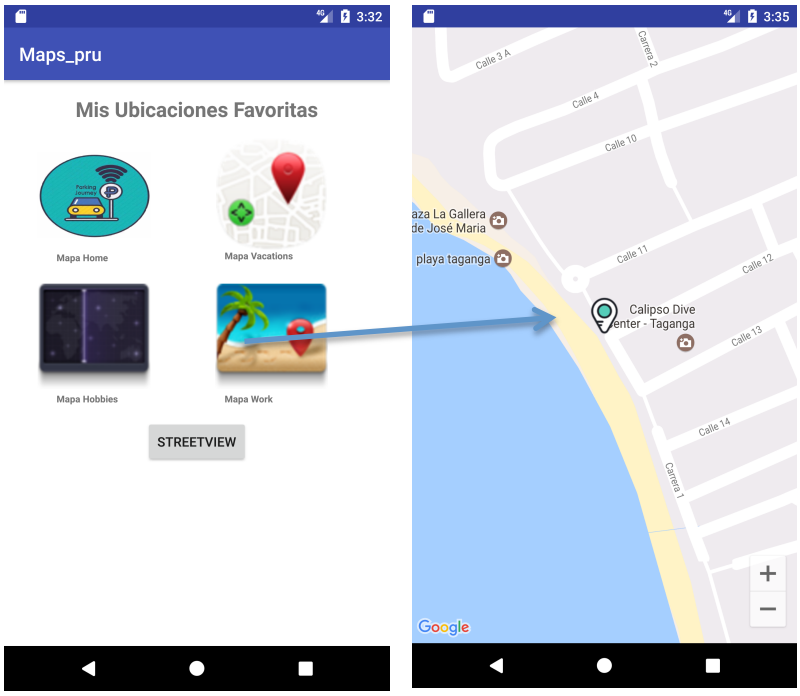

→ Se implementa un botox auxiliar que muestra las mismas direcciones en StreetView, el cual al presionarlo nos lleva a la siguiente actividad =

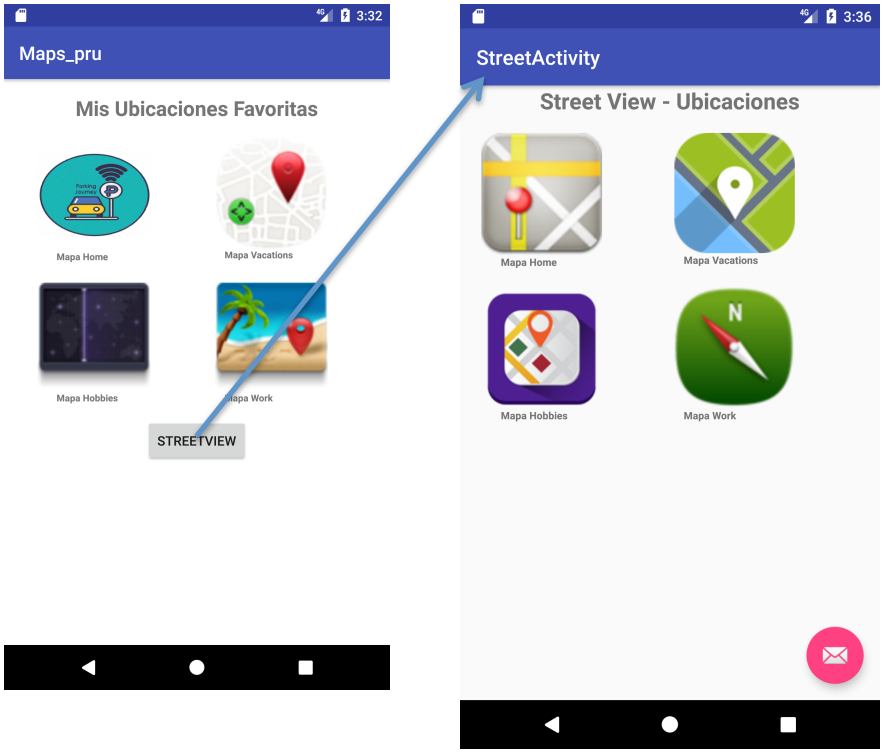
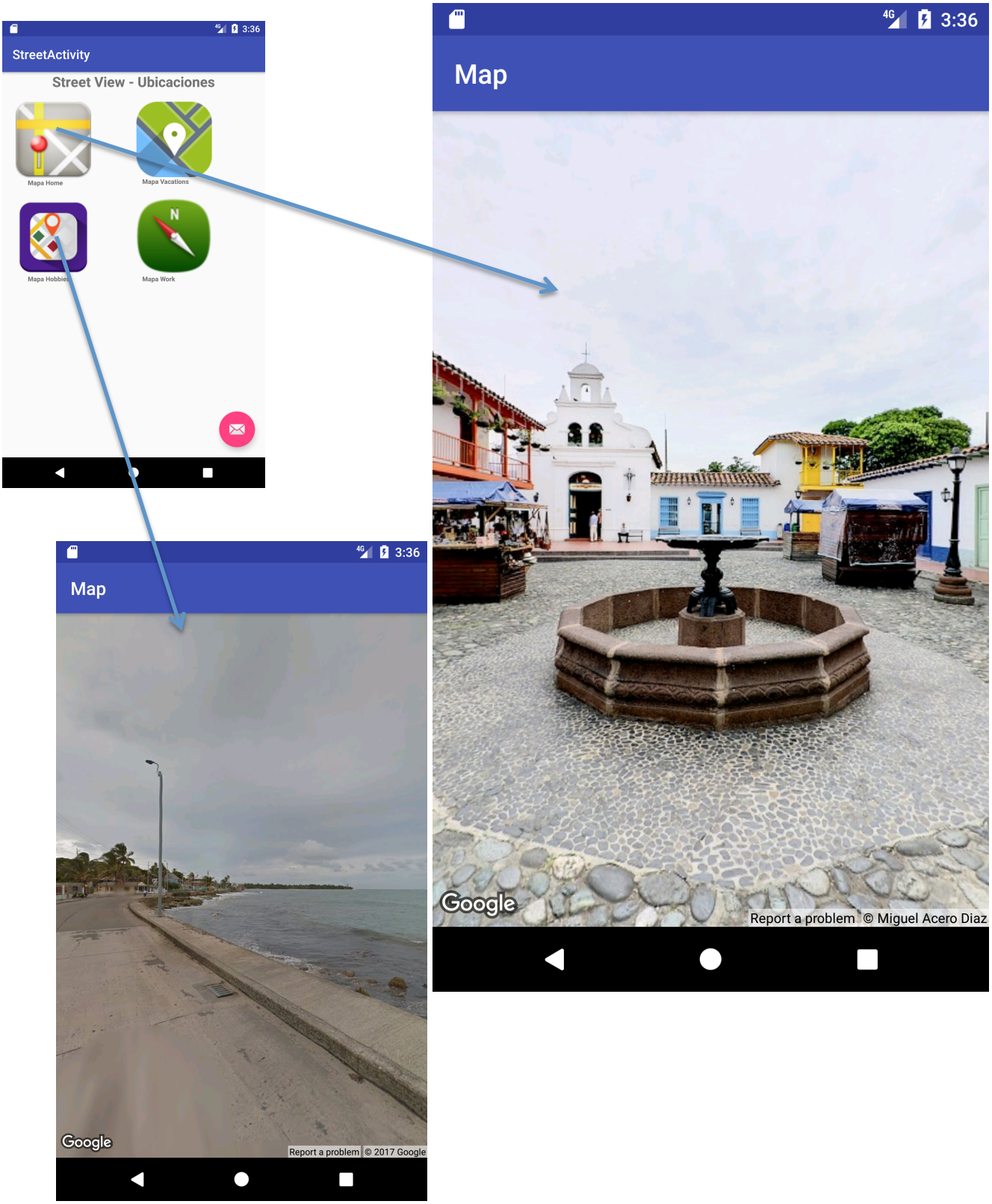
Al Seleccionar cualquiera de los ligares favoritos nos muestra el streetview de ese punto =